# 第 5 章: 発見
# (5.3. 空間データ)

今井耕介 著

『社会科学のためのデータ分析入門 (QSS)』

2026-03-09

# 5.3 空間データ

# 地理空間情報の分析

- **空間データ**: 位置情報（緯度・経度など）を持つデータ。
- **目標**: 現象の地理的な広がりを視覚化し、地域間のパターンや関係を理解する。
- 古典的な例: スノーによるコレラ発生源の特定。

# 5.3.1 R における空間データの扱い

# maps パッケージ: プロットのコード

- R で地図を描画するための標準的なパッケージ。

```
library(maps)
# 1. 米国地図の描画
map(database = "usa")

# 2. 州都のデータ (us.cities) を読み込む
data(us.cities)
# capital == 2 が州都を表す
capitals <- subset(us.cities, capital == 2)

# 3. 州都の位置を地図上にプロット
# cex は点の大きさ、pch は点の形
points(x = capitals$long, y = capitals$lat,
       cex = capitals$pop / 500000, pch = 19, col = "red")
```

# maps パッケージ: 描画結果

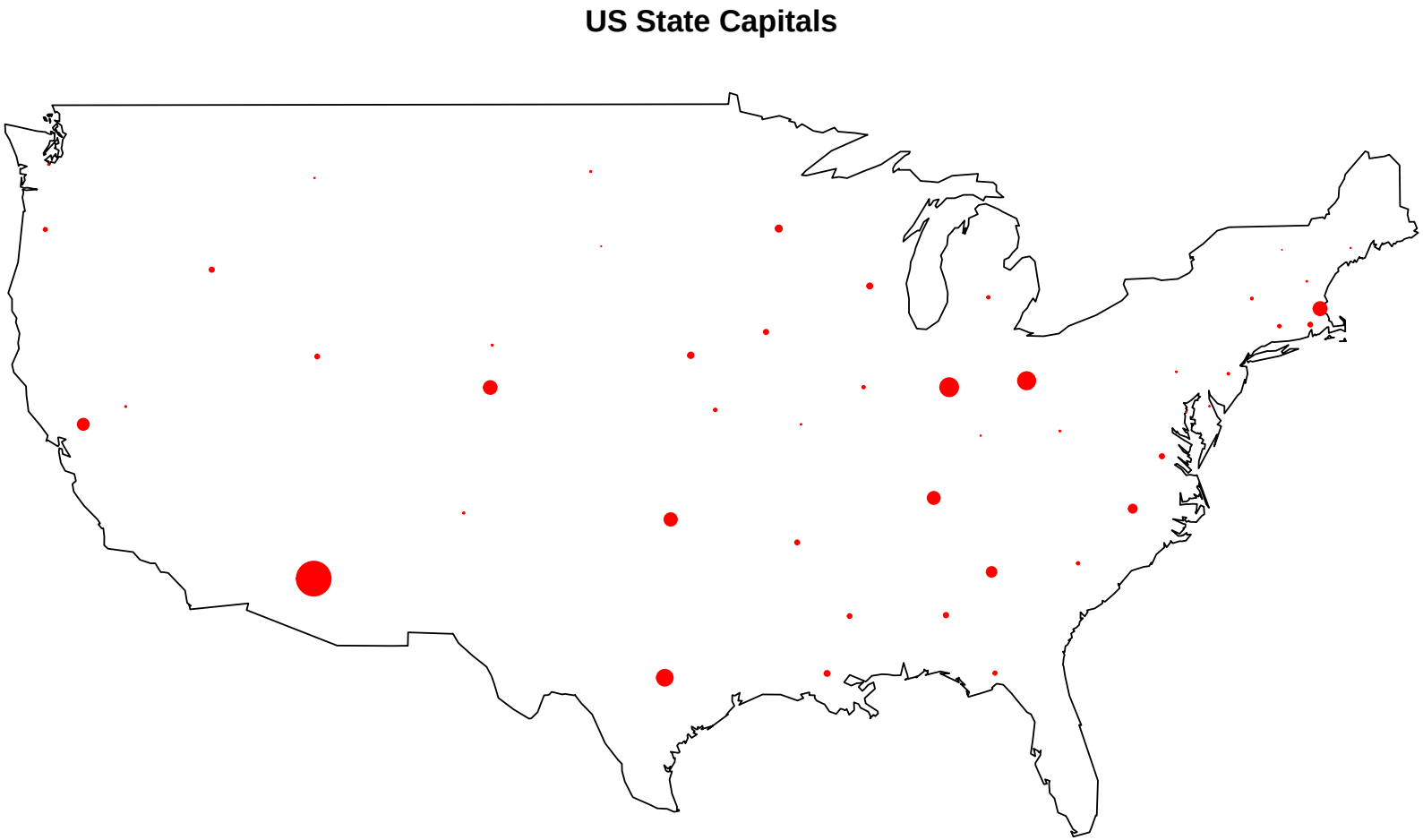

# 特定の地域の拡大: プロットのコード

- regions 引数で特定の州などを指定できます。

```
# 1. カリフォルニア州のみを描画
map(database = "state", regions = "California")

# 2. カリフォルニア州の都市データを抽出
cal.cities <- subset(us.cities, subset = (country.etc == "CA"))

# 3. 人口上位 7 都市を特定し、プロット
top7 <- order(cal.cities$pop, decreasing = TRUE)[1:7]
points(x = cal.cities$long[top7], y = cal.cities$lat[top7], pch = 19)

# 4. 都市名を追加
text(x = cal.cities$long[top7] + 2, y = cal.cities$lat[top7],
     label = cal.cities$name[top7], cex = 0.8)
```

# 特定の地域の拡大: 描画結果

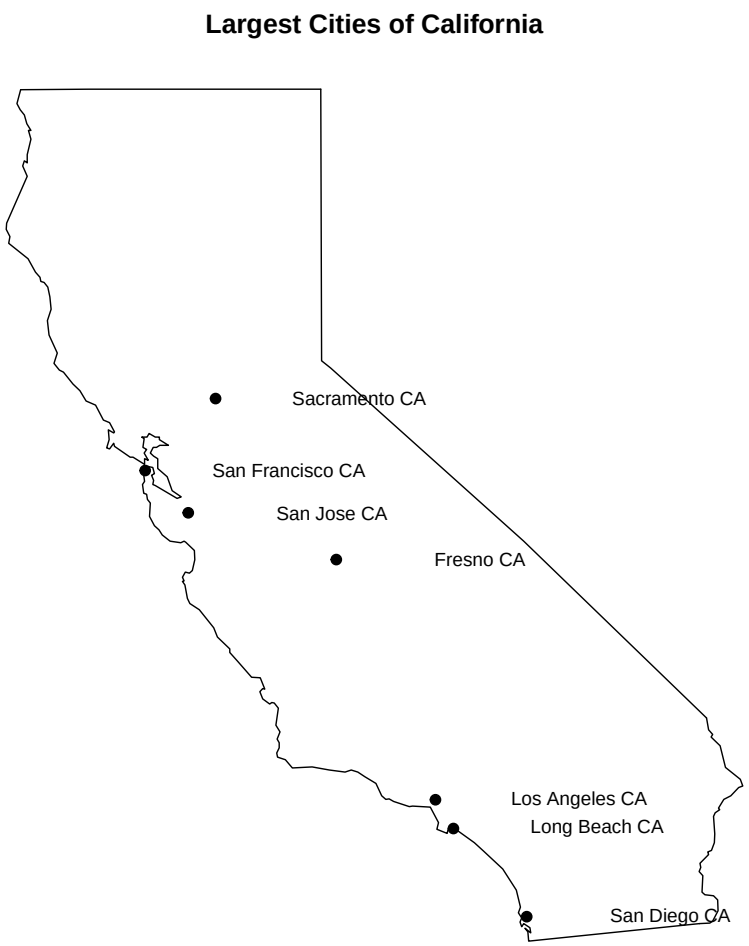

# 5.3.2 R における色の指定

# rgb() 関数と透明度

- rgb() で赤・緑・青の強度 (0〜1) と、透明度 (alpha) を指定できます。

```
# 半透明の青 (alpha=0.5) を作成
blue.trans <- rgb(red = 0, green = 0, blue = 1, alpha = 0.5)

# 重なりを確認するためのプロット
plot(x = c(1, 1.2), y = c(1, 1), xlim = c(0.5, 2), ylim = c(0.5, 1.5),
     pch = 16, cex = 10, col = blue.trans, main = "Transparency Example")
```

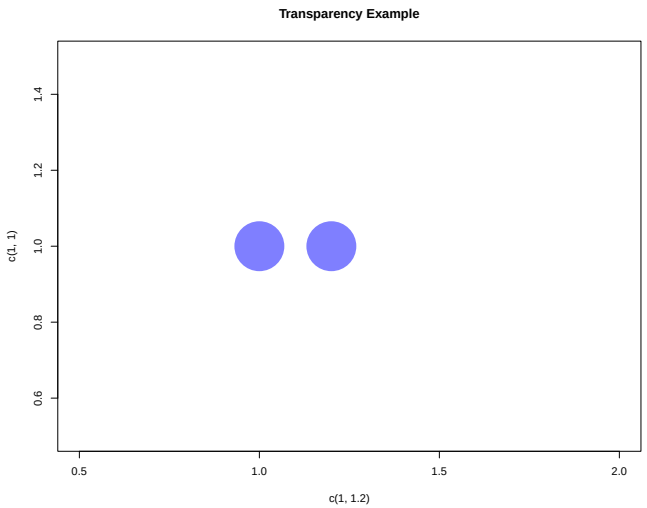

# 5.3.3 米国大統領選挙のマップ

# 州別の色分け (1): 州のリストを作成

- 民主党が勝った州と共和党が勝った州の名前を、それぞれ別々のリストにまとめます。

```
pres08 <- read.csv("pres08.csv")

# 1. オバマ（民主党）が勝った州の名前を取り出す
# Obama > McCain という条件に合う state.name を抽出
blue_states <- pres08$state.name[pres08$Obama > pres08$McCain]

# 2. マケイン（共和党）が勝った州の名前を取り出す
# McCain > Obama という条件に合う state.name を抽出
red_states <- pres08$state.name[pres08$McCain > pres08$Obama]

# リストの最初の方を確認
head(blue_states, n = 5)
```

```
## [1] "California"  "Colorado"    "Connecticut" "D.C."        "Delaware"
```

# 州別の色分け (2): 地図を塗るコード

- 作成したリストを使って、指定した州をまとめて塗りつぶします。

```
library(maps)
# 1. まず米国本土の白地図を描く
map(database = "state")

# 2.「青い州のリスト」に含まれる州を青色 (blue) で一気に塗る
# regions 引数に名前のリストを渡す
map(database = "state", regions = blue_states,
    col = "blue", fill = TRUE, add = TRUE)

# 3.「赤い州のリスト」に含まれる州を赤色 (red) で一気に塗る
map(database = "state", regions = red_states,
    col = "red", fill = TRUE, add = TRUE)
```

# 州別の色分け (3): 選挙結果のマップ

**2008 Election: Red and Blue States**

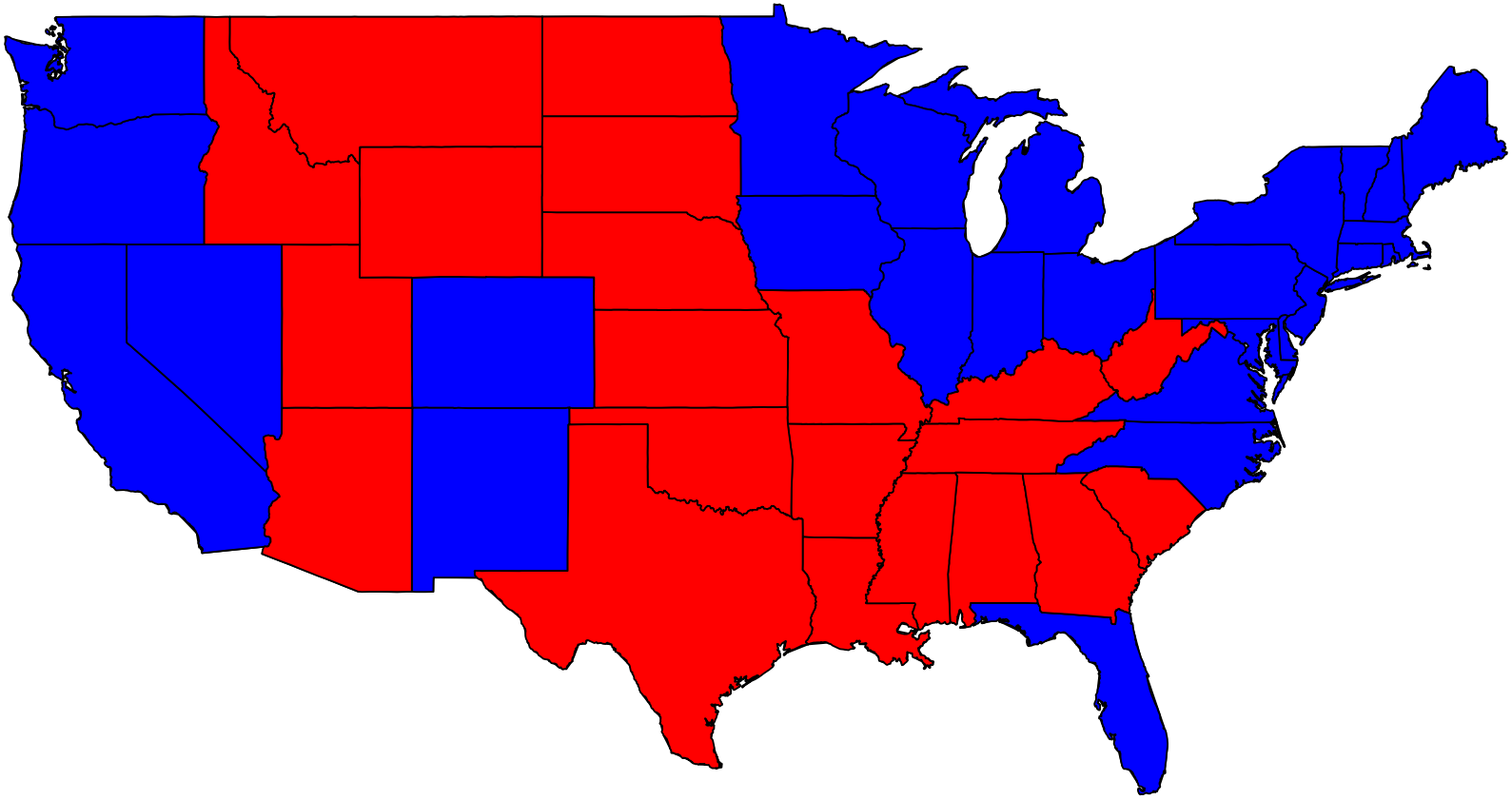

# 5.3.4 ウォルマートの拡大

# 拡大プロセスの視覚化 (1): 準備

```r
walmart <- read.csv("walmart.csv")

# 1. 出店形態に応じた「色の列」をデータに追加する
walmart$col <- NA # 初期化

# 店舗タイプごとに、rgb() で透過色を指定
# Wal-MartStore は赤 (red)
walmart$col[walmart$type == "Wal-MartStore"] <- rgb(1, 0, 0, 0.2)
# SuperCenter は緑 (green)
walmart$col[walmart$type == "SuperCenter"] <- rgb(0, 1, 0, 0.2)
# DistributionCenter は青 (blue)
walmart$col[walmart$type == "DistributionCenter"] <- rgb(0, 0, 1, 0.5)
```

# 拡大プロセスの視覚化 (2): プロットのコード

```
# 1. 白地図を描く
map(database = "state")

# 2. 店舗の位置 (long, lat) を、設定した色 (col) でプロット
# cex (点の大きさ) は、配送センター (DistributionCenter) のみ大きくする
points(walmart$long, walmart$lat, col = walmart$col,
       pch = 19, cex = ifelse(walmart$type == "DistributionCenter", 1, 0.5))

# 3. 凡例を追加
legend("bottomright", legend = c("Store", "Supercenter", "Dist. Center"),
       col = c("red", "green", "blue"), pch = 19, bty = "n", cex = 0.7)
```

# 拡大プロセスの視覚化 (3): ウォルマートの拡大マップ

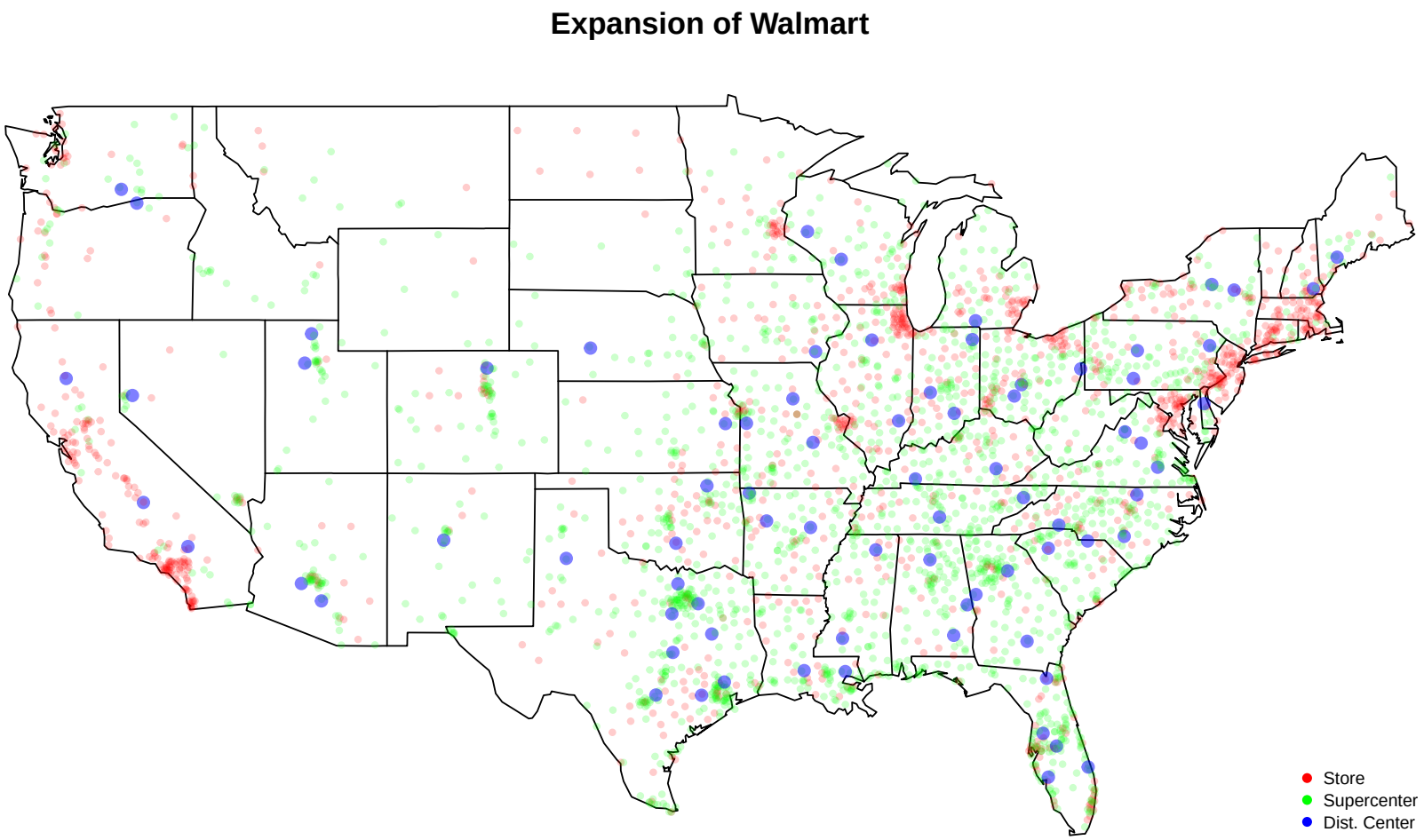

# 5.3.5 まとめ

# まとめ

- **空間分析**: 現象の地理的パターンを視覚化する強力な手法。
- **maps パッケージ**: 基本的な地図描画と、特定地域の拡大が可能。
- **座標とプロット**: 緯度・経度を `points()` 等で地図上に重ねる。
- **色の活用**: `rgb()` と `alpha` を用いて、データの密度や属性を表現する。
- **コロプレスマップ**: 地域（州など）を属性データに基づいて色分けする。